ՊԵՏԱԿԱՆ ԳՈՒՅՔԻ ԿԱՌԱՎԱՐՄԱՆ ԿՈՄԻՏԵ

ՊՐԵՄԻՈՒՄ ԴԱՍԻ ԲԱԶՄԱՖՈՒՆԿՑԻՈՆԱԼ ՀՈՂԱՏԱՐԱԾՔ

EVN - ISAKOV

40.15°N / 44.46°E
Հայաստան, Երևան
PROSPECT24
2025

ԲՈՎԱՆԴԱԿՈՒԹՅՈՒՆ

3-4 Տեղադիրք

5-7 Տեղանքի վերլուծություն

8 Տարածքի միկրոկլիմա

9-11 Շուկայի հետազոտություն

12-13 Ֆինանսական մոդելավորում

14-16 Զարգացում

PROSPECT24 © 2025


Իսակով 23, 25/2, 25/3, 25/4
Մակերես՝ 3.631 հա
Իսակովի պողոտա
Բագրատունյաց պողոտա
Կոորդինատներ:
40.15°N / 44.46°E

ՏԱՐԱԾՔԻ ՌԱԶՄԱՎԱՐԱԿԱՆ ՆԿԱՐԱԳԻՐ

- **Իսակովի պողոտա՝** օդանավակայան - Երևանի կենտրոն հիմնական առանցք
- Նախատեսվող **Իսակով-Արշակունյաց արագընթաց** մայրուղի՝ 6 գոտիով
- Ուղիղ կապ **Յուսիս-Հարավ** մայրուղուն
- Ուղիղ կապ **Կենտրոն, Շենգավիթ և Աջափնյակ** վարչական շրջանների հետ
- Դեպի **Հանրապետության հրապարակ** (Երևանի կենտրոն)՝ **10-15ր**

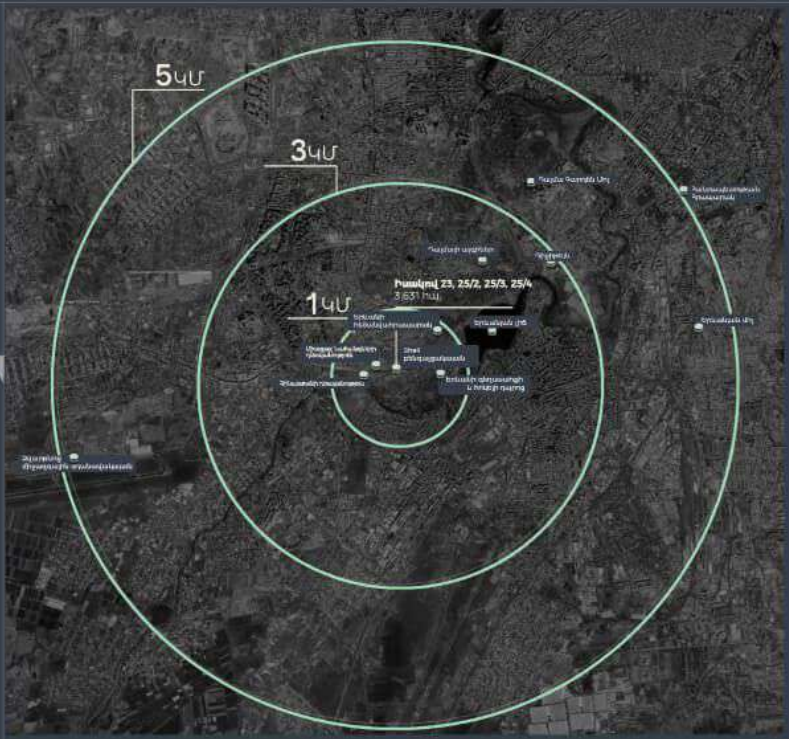

ՃԱՆԱՊԱՐՀԱՅԻՆ ՀԱՍԱՆԵԼԻՈՒԹՅՈՒՆ

Տարածքն ունի ավտոմոբիլային կապ **հիմնական ճանապարհային** հանգույցների հետ, ներառյալ **Բագրատունյաց, Սեբաստիա, Մոնթե Մելքոնյան փողոցները և Հյուսիս -Հարավ** մայրուղին՝ ապահովելով հարմար երթևեկելիություն և ուղիղ հասանելիություն Կենտրոն և այլ վարչական շրջաններ:

Ենթակառուցվածքային պլանային զարգացումները, մասնավորապես **Մոնթե Մելքոնյան փողոցի ընդլայնման և զարգացման նախագիծը**, կխթանեն քաղաքային շարժունակության բարելավումը, կնվազեցնեն ճանապարհային ծանրաբեռնվածությունը և կնպաստեն տրանսպորտային համակարգի շահագործման արդյունավետությանը՝ ի շահ քաղաքի բնակիչների և այցելուների:

ՍՈՏԱԿԱՅՔՈՒՄ ԳՏՆՎՈՒՄ ԵՆ՝

Հողատարածքը գտնվում է մի շարք դեսպանատների և բիզնես կենտրոնների անմիջական հարևանությամբ, ինչը հատկապես նպաստավոր է ինչպես բնակելի, այնպես էլ առևտրային ու ներդրումային նախագծերի իրականացման համար:

Տարածքը ունի զարգացման զգալի ներուժ շնորհիվ իր ռազմավարական դիրքի և բարձր ներդրումային գրավչության:



PROSPECT24 © 2025

ՄՈՏԱԿԱՅՔՈՒՄ ԳՏՆՎՈՒՄ ԵՆ՝

Տարածքը գտնվում է մարզամշակութային և առևտրային մի շարք կենտրոնների մոտակայքում:

Երևանի գեղասահքի և հոկեյի դպրոց

450 մ / 1 ր.



Երևանի հեծանվահրապարակ

350 մ / 1 ր.

Դալմա Գարդեն Մոլ

4.9 կմ / 15 ր.

Երևան Մոլ

5 կմ / 10 ր.

ԿԼԻՄԱ ԵՎ ՕԴԻ ՈՐԱԿ

ՆԵՐԿԱ ԻՐԱՎԻՃԱԿ

226 դիտարկված օրերից՝

- 77% Լավ կամ չափավոր լավ
- 23% Միջինից ցածր

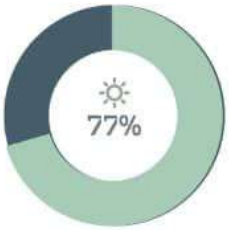

Լավ կամ չափավոր լավ

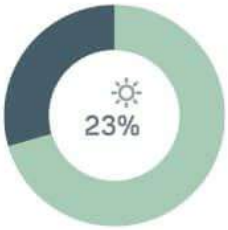

Միջինից ցածր

Օդի մաքրության տեսանկյունից տարածքը բարենպաստ է: 226 դիտարկված օրերից 173-ը գնահատվել են որպես լավ կամ չափավոր լավ:

Տարածքը գտնվում է Հրազդան գետի հարևանությամբ , ինչը նպաստում է կլիմայական պայմանների մեղմմանը: Ավելին, մոտ 1 կմ հեռավորության վրա տեղակայված է նաև Երևանյան լիճը, որը ևս դրական ազդեցություն ունի միկրոկլիմայի վրա:

ՇՈՒԿԱՅԻ ՀԵՏԱԶՈՏՈՒԹՅՈՒՆ

ՀՈՂԱՏԱՐԱԾՔԻ ԱՐԺԵՎՈՐՄԱՆ ՀԻՄՆԱԿԱՆ ԳՈՐԾՈՆՆԵՐ

- Շրջակայքում սահմանափակ կառուցապատման հնարավորություն
- Նախատեսվող աննախադեպ նոր այգի ոկմ հեռավորության վրա
- Ենթակառուցվածքի ցանցի ընդլայնում հողատարածքի շրջակայքում
- Ուղիղ հասանելիություն՝ միջպետական երթուղու
- Անշարժ գույքի նկատմամբ աճող պահանջարկ
- Ուղիղ հասանելիություն «Զվարթնոց» միջազգային օդանավակայանին

PROSPECT24 © 2025

ԳՈՅՈՒԹՅՈՒՆ ՈՒՆԵՑՈՂ ԵՆԹԱԿԱՌՈՒՑՎԱԾՔՆԵՐ

- Գազատար
- Ջրագիծ և կոյուղատար
- Էլեկտրաէներգիայի մնուցման հնարավորություն
- Հեռահաղորդակցման գծեր

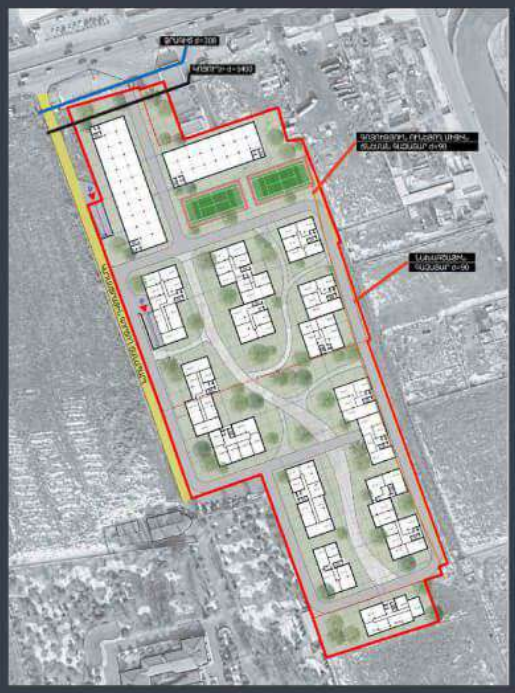

ՀՈՂԱՏԱՐԾՔԻ ԿԱԴԱՍՏՐԱՅԻՆ ԲԱԺԱՆՈՒՄՆԵՐԸ



ԱՎՏՈԿԱՅԱՆԱՏԵՂԻ ՀԱՏԱԿԱԳԻԾ

-1 հարկ

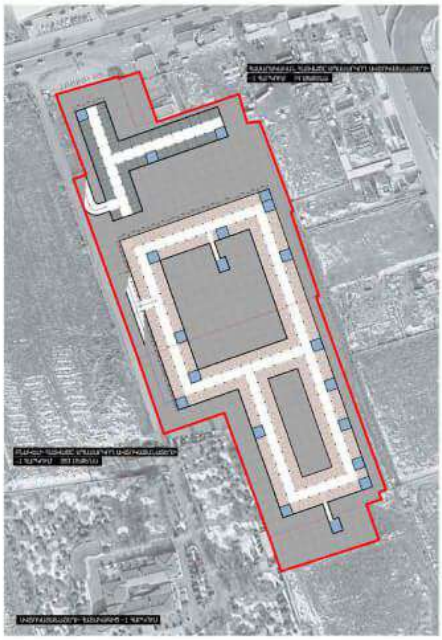

-2 հարկ

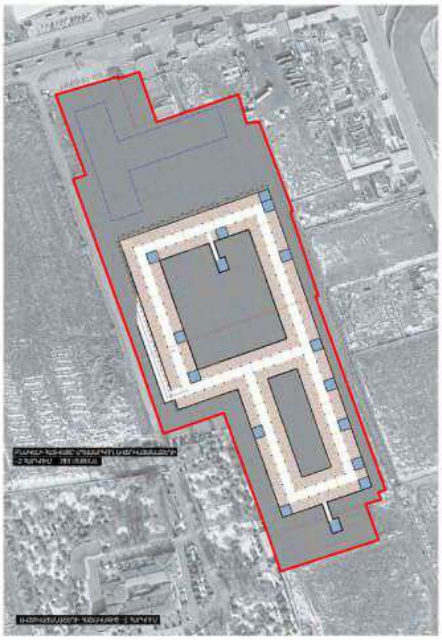
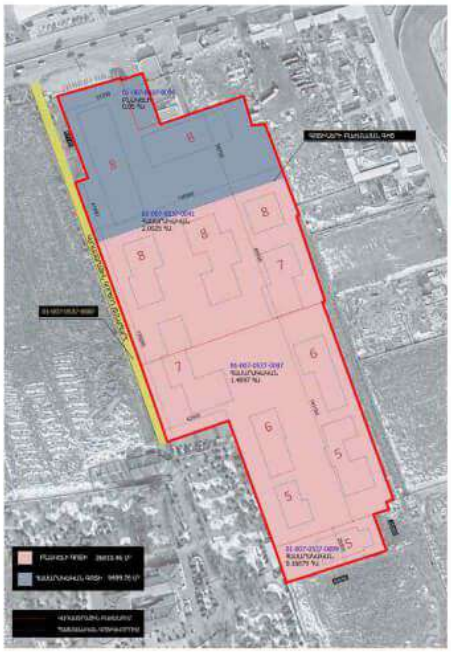
ԳԼԽԱՎՈՐ ՀԱՏԱԿԱԳԻԾ